(1) F

ನಮೂನೆ-3

Acknowledgement/Extract/A-Register

(See rule 20)

ಕರ್ನಾಟಕ ಸರ್ಕಾರ ಪೌರಾಡಳಿತ ನಿರ್ದೇಶನಾಲಯ		ನಗರಸಭೆ, ಮುಧೋಳ ನಮೂನೆ-3 (ನಿಯಮ 20)

ಜಿಲ್ಲೆ : ಬಾಗಲಕೋಟೆ	ನಗರ/ಪಟ್ಟಣ : ಮುಧೋಳ್	ಸ್ವತ್ತಿನ ತರಹೆ : ಖಾಸಗಿ	ದಾಖಲೆ ಸಂಖ್ಯೆ : 25248370

ಸ್ವತ್ತಿನ ಸಂಖ್ಯೆ	ವಾರ್ಡ್ ನ ಸಂಖ್ಯೆ ಮತ್ತು ಹೆಸರು		ಸ್ವತ್ತಿನ ಹಳೆ ಸಂಖ್ಯೆ	ನಿರ್ದರಣಾ ಸಂಖ್ಯೆ	ಸ್ವತ್ತಿನ ವರ್ಗಿಕರಣ (as per A Register)	ಸ್ವತ್ತಿನ ಪ್ರಕಾರ
36-555-14	15	15	ಬಿ ನಂ 23 ಪೇ ನಂ 80 ಅ ನಂ 7807	ಆರ್ ಟಿ ಎಸ್ ನಂ-504 ಕ ಪ್ಲಾಟ ನಂ-14	ಅಧಿಕೃತ	ನಿವೇಶನ

ಸ್ವತ್ತಿನ ವಿಳಾಸ	ನಿವೇಶನದ ಅಳತೆ (ಮೀ.)	ನಿವೇಶನದ ವಿಸ್ತೀರ್ಣ (ಚ.ಮೀ)	ಕಟ್ಟಿಡದ ಪ್ಲಿಂಥ್ ಏರಿಯ (ಚ.ಮೀ)
14,ಜಯನಗರ ಮುಧೋಳ್, ಬಾಗಲಕೋಟೆ	ಪೂರ್ವ-ಪಶ್ಚಿಮ X ಉತ್ತರ-ದಕ್ಷಿಣ - X -	108	NA

ಅಪಾರ್ಟ್ ಮೆಂಟ್ / ಬಹು-ಮಾಲೀಕತ್ವದ ಕಟ್ಟಿಡ ಗೆ ಮಾತ್ರ

ಅವಿಭಜಿತ ನಿವೇಶನದ ಸ್ವತ್ತಿನ ಸಂಖ್ಯೆ	ಮಹಡಿ ಸಂಖ್ಯೆ/ಬ್ಲಾಕ್ ಹೆಸರು	ಫ್ಲಾಟ್ ಸಂಖ್ಯೆ	ವಿಸ್ತೀರ್ಣ (ಚ.ಮೀ) ಕಾರ್ಪೆಟ್	ಅಡಿಷನಲ್	ಸೂಪರ್ ಬಿಲ್ಟ್ ಅಪ್	ಅವಿಭಜಿತ ನಿವೇಶನ ರೀತಿ	ತರಹೆ	ಪಾರ್ಕಿಂಗ್ ಲಭ್ಯತೆ/ಯೂನಿಟ್ಸ್/ಏರಿಯ	ಅನುಭೋಗ	ಮೇಲ್ಮಾವಣೆ/ನೆಲದ ವಿಧ/ಬಳಸಿರುವ ಮರ
NA	NA	NA	NA	NA	NA	NA	NA	NA / NA / NA	NA	NA/NA/NA

ಕಟ್ಟಿಡಗೆ ಮಾತ್ರ

ಮಹಡಿ ಸಂಖ್ಯೆ	ವಿಸ್ತೀರ್ಣ(ಚ.ಮೀ)	ತರಹೆ	ಅನುಭೋಗ	ಮೇಲ್ಮಾವಣೆ ತರಹೆ	ನೆಲದ ವಿಧ	ಬಳಸಿರುವ ಮರ	ನಿರ್ಮಾಣದ/ ಕೆಡವಿದ	ವರ್ಷ
NA	NA	NA	NA	NA	NA	NA	NA	NA

ಚಕ್ಕುಬಂದಿ – ಉತ್ತರ	ಚಕ್ಕುಬಂದಿ – ಪೂರ್ವ	ಚಕ್ಕುಬಂದಿ – ಪಶ್ಚಿಮ	ಚಕ್ಕುಬಂದಿ – ದಕ್ಷಿಣ
ಪ್ಲಾಟ ನಂ-13	ರಸ್ತೆ	ಲಾ ಗೂ ರಿ ಸ ನಂ-503	ಪ್ಲಾಟ ನಂ-15

ಸ್ವಾಧೀನತೆಗೆ ಪೂರಕ ದಾಖಲೆಗಳು :	ಹಕ್ಕು ಬದಲಾವಣೆ / ಕಡತದ ಸಂಖ್ಯೆ	ಸ್ವತ್ತಿನ ಛಾಯಾಚಿತ್ರ	ಹಕ್ಕುಗಳು
ಇತರೆ, ಇತರೆ, ಇತರೆ	VERI		NA

ಕ್ರ. ಸಂ.	ಮಾಲೀಕರ ಹೆಸರು	ತಂದೆ / ತಾಯಿ / ಗಂಡ / ಹೆಂಡತಿ/ಪೋಷಕರ ಹೆಸರು	ಮಾಲೀಕರ ಗುರುತಿನ ದಾಖಲೆ	ವಿಳಾಸ	ಮಾಲೀಕರ ಛಾಯಾಚಿತ್ರ
1	ಶ್ರೀ ಸಿದ್ದು ಎ ಸಿದ್ದಪ್ಪ ತಂ ಸದಾಶಿವ ಬಟಕುರ್ಕಿ	ಬಿನ್ ತಂ ಸದಾಶಿವ	ಪ್ಯಾನ್ ಕಾರ್ಡ್ xxxxxxxx124C	ಜಯನಗರ ಮುಧೋಳ್, ಬಾಗಲಕೋಟೆ	
2	ಶ್ರೀ ಸುರೇಶ ಬಸಪ್ಪ ಮುಳ್ಳೂರ	ಬಿನ್ ಬಸಪ್ಪ	ಪ್ಯಾನ್ ಕಾರ್ಡ್ xxxxxxxx691C	ಜಯನಗರ ಮುಧೋಳ್, ಬಾಗಲಕೋಟೆ	
3	ಶ್ರೀ ಯಮನಪ್ಪ ರಾಮಪ್ಪ ಕೋಳಿ	ಬಿನ್ ರಾಮಪ್ಪ	ಪ್ಯಾನ್ ಕಾರ್ಡ್ xxxxxxxx469J	ಜಯನಗರ ಮುಧೋಳ್, ಬಾಗಲಕೋಟೆ	

ಕ್ರ. ಸಂ.	ಅನುಭೋಗದಾರರು	ತಂದೆ / ತಾಯಿ / ಗಂಡ / ಹೆಂಡತಿ/ಪೋಷಕರ ಹೆಸರು	ಋಣಗಳು
1	NA	NA	NA

ಗ್ರಾಮ - ಸರ್ವೆ ನಂಬರ್	ಪ್ರಕರಣ- 111 ರಂತೆ ಹಕ್ಕು ವರ್ಗಾವಣೆ ನೋಟೀಸ್ ದಿನಾಂಕ
NA	NA

ಎಸ್.ಎ.ಎಸ್ ವಿವರ ಪಟ್ಟಿ ಸಲ್ಲಿಸಿದ ದಿನಾಂಕ ಮತ್ತು ಸಂಖ್ಯೆ	ಬ್ಯಾಂಕಿನ ಹೆಸರು	ತೆರಿಗೆ ಸಂದಾಯದ ದಿನಾಂಕ	ಸಂದಾಯವಾದ ಒಟ್ಟು ಆಸ್ತಿ ತೆರಿಗೆ ಮೊತ್ತ	ಸಂದಾಯವಾದ ಒಟ್ಟು ಉಪಕರದ ಮೊತ್ತ	ಅಂತಿಮ ಆಸ್ತಿ ತೆರಿಗೆ ಸಂದಾಯವಾದ ಮುಂಕಾಸು ವರ್ಷ
15595MDLOC07062025 , 09-06-2025	HDFC BANK	09-06-2025	261	68	2025-26

ನಮೂನೆ ವಿತರಿಸಿದ ದಿನಾಂಕ	ನಮೂನೆ ಶುಲ್ಕ	ನಮೂನೆ ಪತ್ರದ ರಸೀದಿ ಸಂಖ್ಯೆ	ನಮೂನೆ ವಿತರಿಸಿದವರು	ನಮೂನೆ ವಿತರಿಸಿದ ಸ್ಥಳ
01/07/2025 20:07:22	100	149723	bc2_mdl	ಮುಧೋಳ್

ಡಿಜಿಟಲ್ ಸಹಿ
ನಗರಸಭೆ, ಮುಧೋಳ

ವಿಶೇಷ ಸೂಚನೆ :-

Sl.No 1: ಆಸ್ತಿಯ ಹಕ್ಕನ್ನು ಸಾಧಿಸಲು ಸೂಕ್ತ ದಾಸ್ತಾವೇಜುಗಳು / ಮತ್ತು ಕ್ರಮಬದ್ಧ ಕಟ್ಟಡ ಪರವಾನಿಗೆ/ಸೂಕ್ತ ಪ್ರಾಧಿಕಾರದ ಅನುಮೋದಿತ ರೂಪರೇಖೆಯ ಗೈರುಹಾಜರಿಯಲ್ಲಿ ಕೇವಲ ನಮೂನೆ III ರಲ್ಲಿನ ಪ್ರಪತ್ರ ಮಾತ್ರ ಕ್ರಮಬದ್ಧ ದಾಖಲಾತಿಯೆಂದು ಭಾದಿತ ವ್ಯಕ್ತಿಯಾಗಲಿ ಅಥವಾ ಆರ್ಥಿಕ ಸಂಸ್ಥೆಯಾಗಲಿ ಭಾವಿಸತಕ್ಕದ್ದಲ್ಲ.

ಟಿಪ್ಪಣಿ :- ವಿದ್ಯುನ್ಮಾನ ಸಹಿಯನ್ನು ಹೊಂದಿದ್ದು ಕೈ ಬರಹದ ಸಹಿಯ ಅಗತ್ಯವಿರುವುದಿಲ್ಲ ಹಾಗೂ ನೈಜತೆಯನ್ನು ಪರಿಶೀಲಿಸಲು ವೆಬ್ ಸೈಟ್ (https://eaasthi.karnataka.gov.in) ಪ್ರವೇಶದೊಂದಿಗೆ ಆಸ್ತಿ ಸಂಖ್ಯೆಯನ್ನು ನಮೂದಿಸುವುದು.

(2) NA

ಕಂದಾಯ ಇಲಾಖೆ

ಉಪವಿಭಾಗಾಧಿಕಾರಿಗಳ ಕಾರ್ಯಾಲಯ ಬಾಗಲಕೋಟೆ ಜಿಲ್ಲೆ.

ದಿನಾಂಕ :30/01/2024

ನಂಬರ್ : SB6472

ಅಧಿಕೃತ ಜ್ಞಾಪನ

ವಿಷಯ : ಬಾಗಲಕೋಟೆ ಜಿಲ್ಲೆ, ಮುಧೋಳ ತಾಲ್ಲೂಕು, ಮುಧೋಳ ಹೋಬಳಿ, ಮುಧೋಳ ಗ್ರಾಮದ 504/2ಅ/1ಸ.ನಂಬರಿನ 1.14.0.00 ಎಕರೆಗುಂಟೆ ವಿಸ್ತೀರ್ಣದ ವ್ಯವಸಾಯದ ಜಮೀನನ್ನು, ಮಾಸ್ಟರ್ ಪ್ಲಾನ್ ಆಧಾರಿತ ದೀರ್ಘ ಭೂಪರಿವರ್ತನೆ ಆದೇಶ ಹೊರಡಿಸುವ ಬಗ್ಗೆ.

ಆದೇಶಿಸಿ :

1. Modhal ಯೋಜನಾ ಪ್ರಾಧಿಕಾರದ ನಿರಾಕ್ಷೇಪಣಾ ಪತ್ರ.
2. ಭೂ ಪರಿವರ್ತನಾ ಶುಲ್ಕ ರೂ 29403 ಗಳನ್ನು, ಚಲನ್ ನಂ: IE012400290069483 3 ದಿನಾಂಕ : 18/01/2024 ರಂತೆ ಸಂಸ್ಕರಣಾ ಶುಲ್ಕ ರೂ 55 ಗಳನ್ನು, ಚಲನ್ ನಂ: IE012400290069484 1 ದಿನಾಂಕ : 18/01/2024 ರಂತೆ ಸಂರಕ್ಷಣಾ ಶುಲ್ಕ ರೂ. : 0 ರಂತೆ ಹಾಗೂ ,ದಂಡ ಶುಲ್ಕ ರೂ : 0 ರಂತೆ ಒಟ್ಟು ರೂ. 29458 ಗಳನ್ನು ಅಜಾಮಗೆ ಅರ್ಜಿದಾರರು ಜಮಾ ಮಾಡಿರುತ್ತಾರೆ.

<<<<<>>>>>

ಕರ್ನಾಟಕ ಭೂ ಕಂದಾಯ ಅಧಿನಿಯಮ 1964 ರ ಕಲಂ 95 (2) ರಡಿಯಲ್ಲಿ, ಶ್ರೀ/ಶ್ರೀಮತಿ ಸುರೇಶ ಬಸಪ್ಪ ಮುಳ್ಳೂರ ಬಿನ್ ಬಸಪ್ಪ ರವರ ಅರ್ಜಿಯನ್ನು ಪರಿಗಣಿಸಿ ಮುಧೋಳ ತಾಲ್ಲೂಕು, ಮುಧೋಳ ಹೋಬಳಿ, ಮುಧೋಳ ಗ್ರಾಮದ 504/2ಅ/1 ಸ.ನಂಬರಿನ 1.14.0.00 ಎಕರೆ/ಗುಂಟೆ ವಿಸ್ತೀರ್ಣದಲ್ಲಿ 1.14.0.00 ವಿಸ್ತೀರ್ಣವು ಸ್ಥಳೀಯ ಯೋಜನೆ ಪ್ರದೇಶದೊಳಗೆ ಇದ್ದು, ಮಾಸ್ಟರ್ ಪ್ಲಾನಿನಲ್ಲಿ ಸದರಿ ಜಮೀನು Layout - Residential ಅಭಿವೃದ್ಧಿಗೆ, ನಿರ್ದಿಷ್ಟಪಡಿಸಿದ್ದು, ಈ ಬಗ್ಗೆ ಅಧ್ಯಾಯ (1) ರಂತೆ ಸಂಬಂಧಪಟ್ಟ ಪ್ರಾಧಿಕಾರದ ನಿರಾಕ್ಷೇಪಣಾ ಪತ್ರ ಸಲ್ಲಿಸಿ ತಾವು ಆದೇ ಅಭಿವೃದ್ಧಿಗೆ, ಅಂದರೆ Layout - Residential ಅಭಿವೃದ್ಧಿಕ್ಕಾಗಿ ಅಭಿಯೋಗಿಸಿಕೊಳ್ಳುವುದಾಗಿ ತಿಳಿಸಿದ್ದು, ಅದರಂತೆ ಕಲಂ 95 (4) ಮತ್ತು 95 (7) ರ ಪರಂತುಗಳು ಹಾಗೂ ಕರ್ನಾಟಕ ಭೂ ಕಂದಾಯ (ತಿದ್ದುಪಡಿ) ನಿಯಮಗಳು 1966 ನಿಯಮ 107 (1) ರಂತೆ ಶುಲ್ಕ ವಿಧಿಸಿದ್ದು, ಅಧ್ಯಾಯ (2) ರಂತೆ ಅರ್ಜಿದಾರರು ಸದರಿ ಶುಲ್ಕವನ್ನು ಪಾವತಿಸಿರುವ ಹಿನ್ನಲೆಯಲ್ಲಿ, ತಾಲ್ಲೂಕು, ಮುಧೋಳ ಹೋಬಳಿ, ಮುಧೋಳ ಗ್ರಾಮದ 504/2ಅ/1 ಸ.ನಂಬರಿನ 1.14.0.00 ಎಕರೆಗುಂಟೆ ವಿಸ್ತೀರ್ಣದಲ್ಲಿ, 1.14.0.00 ಎಕರೆ/ಗುಂಟೆ ವಿಸ್ತೀರ್ಣವು Layout - Residential ಅಭಿವೃದ್ಧಿಕ್ಕಾಗಿ ಕೆಳಕಂಡ ಷರತ್ತುಗಳಿಗೆ ಒಳಪಟ್ಟು, ಭೂಪರಿವರ್ತನೆ ಆದೇಶವನ್ನು ಹೊರಡಿಸಲಾಗಿದೆ.

1. ಈ ಭೂಮಿಯು ಯಾವ ಅಭಿವೃದ್ಧಿಕ್ಕಾಗಿ ಪರಿವರ್ತನೆಯಾಗಿದೆಯೋ ಆ ಅಭಿವೃದ್ಧಿಗೆ, ಅಭಿಯೋಗಿಸಿಕೊಳ್ಳಲು ಸಕ್ಷಮ ಪ್ರಾಧಿಕಾರಿಯಿಂದ, ಅಂದರೆ/ ಅಧ್ಯಕ್ಷರು, ಮಂಡಳಿ ಸಿಎಂಸಿ/ಟಿಎಂಸಿ/ಪಾಲಿಕೆ, ನಿಯಂತ್ರಣ ಮಂಡಳಿ/ಗ್ರಾಮ ಪಂಚಾಯಿತಿಗಳಿಂದ ಮಂಜೂರಾತಿಯನ್ನು ಪಡೆಯದೆ ಹೊರತು ಈ ಆದೇಶವು ಅಮಧ್ಯವರ್ತಿದಾರರಿಗೆ ಯಾವುದೇ ಹಕ್ಕನ್ನು ನೀಡುವುದಿಲ್ಲ.

2. ಈ ಭೂಪರಿವರ್ತನೆ ಜಮೀನನ್ನು Layout - Residential ಅಭಿವೃದ್ಧಿಕ್ಕಾಗಿ ಮಾತ್ರ ಅಭಿಯೋಗಿಸಿಕೊಳ್ಳತಕ್ಕದ್ದು, ಈ ಜಮೀನನ್ನು ಪೂರ್ವಾನುಮತಿ ಇಲ್ಲದೆ ಬೇರೆ ಅಭಿವೃದ್ಧಿಕ್ಕಾಗಿ ಅಭಿಯೋಗಿಸತಕ್ಕದ್ದಲ್ಲ.

3. ಈ ಜಮೀನಿನಲ್ಲಿ ಅಭಿವೃದ್ಧಿಪಡಿಸುವ ಬಡಾವಣೆ ನಕ್ಷೆ, ಹಾಗೂ ಪರವಾನಗಿ ಇತ್ಯಾದಿಗಳನ್ನು Modhal (ಪ್ರಾಧಿಕಾರ / ನಗರಪಾಲಿಕೆ/ಇತ್ಯಾದಿ) ರವರಿಂದ ಅನುಮೋದಿಸಿಕೊಂಡು, ಆ ನಂತರ ಅನುಮೋದನೆಗೊಂಡ ನಕ್ಷೆಗೆ ಅನುಗುಣವಾಗಿ ಕಟ್ಟಡಗಳನ್ನು ಕಟ್ಟುವುದು. ಸದರಿ ಜಮೀನಿನಲ್ಲಿ ಲೇಔಟ್ ಪ್ಲಾನಿಗೆ ಅನುಮೋದನೆ ಪಡೆಯದೆ ಪರಭಾರೆ ಮಾಡತಕ್ಕದ್ದು

4. ಇತರ ಅವಶ್ಯವಾದ ರಸ್ತೆ, ಚರಂಡಿ, ರಸ್ತೆ ಮಾರ್ಜಿನ್, ಖಾಲಿ ಜಾಗ ಇತ್ಯಾದಿಗಳನ್ನು (ಪ್ರಾಧಿಕಾರ / ನಗರಪಾಲಿಕೆ/ಇತ್ಯಾದಿ) ರವರಿಂದ ಅನುಮೋದಿಸಿದ ಬಡಾವಣೆ ನಕ್ಷೆ ಪ್ರಕಾರ ಹಾಗೂ ನಿರ್ದಿಷ್ಟಪಡಿಸಿದ ನಿಯಮಗಳ ರೀತ್ಯ ಸದರಿ ಅಭಿವೃದ್ಧಿಕ್ಕಾಗಿ ಕಾಯ್ದಿರಿಸತಕ್ಕದ್ದು.

5. ಸಾರ್ವಜನಿಕ ಹಿತದೃಷ್ಟಿಯಿಂದ ಸದರಿ ಜಮೀನಿನಲ್ಲಿ ನಿವೇಶನದಾರರಿಗೆ ನೀರಿನ ಸೌಲಭ್ಯಗಳಾದ ಎತ್ತುಪಟ್ಟಿ, ನೀರು ಸರಬರಾಜು ಒಳಚರಂಡಿ ವ್ಯವಸ್ಥೆ, ಇತ್ಯಾದಿಗಳನ್ನು ಅರ್ಹರಿಗೆ ನ್ಯಾಯಸಮ್ಮತವಾದ ಹಾಗೂ ಭದ್ರತೆಗಳ ಅಭಿವೃದ್ಧಿಯಿಂದ ಎಲ್ಲಾ ಸೌಲಭ್ಯಗಳನ್ನು ಇತರರು ರೀತ್ಯ ಒದಗಿಸಿಕೊಡುವುದು ಅರ್ಜಿದಾರರ ಜವಾಬ್ದಾರಿಯಾಗಿರುತ್ತದೆ.

6. ಸರ್ಕಾರದ ಆದೇಶ ನಂ:ಸಿಡಬ್ಲ್ಯೂಡಿ 7556-665-ಆರ್ ಮತ್ತು ಬಿ-6-54-5 ಮತ್ತು ಕೇಂದ್ರ ಸರ್ಕಾರದ ಸಾರಿಗೆ ಇಲಾಖೆಯ ಪತ್ರ ನಂ ಎಲ್:7(11)67, ದಿನಾಂಕ:1-1-1966 ರಂತೆ ಈ ಜಮೀನಿನಲ್ಲಿ ಕಟ್ಟಲು ಅಭಿವೃದ್ಧಿಪಡಿಸುವ ಕಟ್ಟಡವು ರಾಷ್ಟ್ರೀಯ ಹಾಗೂ ರಾಜ್ಯ ಹೆದ್ದಾರಿಗೆ ಸಂಬಂಧಿಸಿದಂತೆ ರಸ್ತೆಯ ಮಧ್ಯಭಾಗದಿಂದ 40 ಮೀಟರ್ ಗಳ ಅಂತರವನ್ನು ಮತ್ತು ಜಿಲ್ಲಾ ಹೆದ್ದಾರಿಗೆ ಸಂಬಂಧಿಸಿದಂತೆ ರಸ್ತೆಯ ಮಧ್ಯಭಾಗದಿಂದ 25 ಮೀಟರ್ ಗಳ ಅಂತರವನ್ನು ಕಾಯ್ದಿರಿಸಬೇಕು ಹಾಗೂ ಈ ಖಾಲಿ ಪ್ರದೇಶದಲ್ಲಿ ಯಾವುದೇ ಕಟ್ಟಡವನ್ನು ಕಟ್ಟತಕ್ಕದ್ದಲ್ಲ.

7. ಈ ಭೂ ಪರಿವರ್ತನಾ ಜಮೀನಿನಲ್ಲಿ ಸ್ಥಾಪಿಸಲಾಗುವ ಕೈಗಾರಿಕಾ ಘಟಕಗಳ ಹೊಗೆ ಅಥವಾ ಇತರ ಕಲ್ಮಷಗಳನ್ನು ಪರಿಣಾಮಕಾರಿಯಾಗಿ ತಡೆಗಟ್ಟಿ, ಸಾರ್ವಜನಿಕರ ಆರೋಗ್ಯಕ್ಕೆ, ಯಾವುದೇ ರೀತಿಯ ಹಾನಿಯಾಗದಂತೆ ಹಾಗು ಪರಿಸರ ಮಾಲಿನ್ಯವಾಗದಂತೆ ನೋಡಿಕೊಳ್ಳತಕ್ಕದ್ದು. ಕೈಗಾರಿಕಾ ಅಭಿವೃದ್ಧಿಕ್ಕಾಗಿ ಭೂ ಪರಿವರ್ತನೆ ಜಮೀನಿನಲ್ಲಿ ಸ್ಥಾಪಿಸುವ ಕೈಗಾರಿಕಾ ಘಟಕಗಳು ಕರ್ನಾಟಕ ಮಾಲಿನ್ಯ ನಿಯಂತ್ರಣ ಮಂಡಳಿ/ಪರಿಸರ ಇಲಾಖೆಗಳ ಅನುಮತಿ ಹೊಂದಿರತಕ್ಕದ್ದು.

8. ಈ ಭೂ ಪರಿವರ್ತನೆ ಆದೇಶ ಪಡೆಯಲು ಯಾವುದೇ ಸುಳ್ಳು, ಮಾಹಿತಿ ಅಥವಾ ದಾಖಲೆ ನೀಡಿದಲ್ಲಿ, ಈ ಆದೇಶ ಯಾವುದೇ ಸೂಚನೆ ನೀಡದೆ ತಕ್ಷಣವೆ ಅಸಿಂಧುವಾಗುವುದು ಹಾಗು ಸೂಚನೆ ನೀಡದೆ ರದ್ದುಗೊಳಿಸಲಾಗುವುದು.

9. ಮೇಲ್ಕಂಡ ಯಾವುದೇ ಷರತ್ತುಗಳನ್ನು ಉಲ್ಲಂಘಿಸಿದಲ್ಲಿ, ಈ ಭೂ ಪರಿವರ್ತನೆ ಆದೇಶ ಯಾವುದೇ ಸೂಚನೆ ನೀಡದೆ ರದ್ದುಗೊಳಿಸಲಾಗುವುದು ಮತ್ತು ಕರ್ನಾಟಕ ಭೂಕಂದಾಯ ಕಾಯ್ದೆ, 1964 ರ ಕಲಂ 96 ರಂತೆ ದಂಡ ಶುಲ್ಕವನ್ನು ವಿಧಿಸಲು ಮುಂದಿನ ಕ್ರಮ ತೆಗೆದುಕೊಳ್ಳಲಾಗುವುದು.

ಅಲ್ಲದೆ ಈ ಜಮೀನಿನಲ್ಲಿ ಅನಧಿಕೃತವಾಗಿ ಕಟ್ಟಿದ ಕಟ್ಟಡಗಳನ್ನು ಯಾವುದೇ ಪರಿವಾರ ನೀಡದೆ ತೆರವುಗೊಳಿಸಲು ಕ್ರಮ ತೆಗೆದುಕೊಳ್ಳಲಾಗುವುದು. ಹಾಗೂ ಅದಕ್ಕೆ ತಗಲುವ ವೆಚ್ಚವನ್ನು ಭೂಕಂದಾಯ ಬಾಕಿ ಎಂದು ಖಾತೆದಾರರಿಂದ ವಸೂಲಿ ಮಾಡಲಾಗುವುದು.

ಷರತ್ತುಗಳು ಷರತ್ತುಗಳು

1. ಈ ಭೂ ಪರಿವರ್ತನೆ ಆದೇಶವು ಮುಂದಿನ ಆದೇಶದವರೆಗೂ ಶಾಶ್ವತವಾಗಿ ಮಾನ್ಯವಾಗಿರುತ್ತದೆ. ಭೂ ಪರಿವರ್ತನೆಯ ಆದೇಶ ಬದಲಾವಣೆಯಾಗಬೇಕಾದರೆ ಸೆಕ್ಷನ್ 97 ರ ಪ್ರಕಾರ ಹೊಸ ಆದೇಶ ಪಡೆಯತಕ್ಕದ್ದು.

2. ಷರತ್ತು (ಎ) ರಲ್ಲಿ ತಿಳಿಸಿರುವಂತೆ ಭೂ ಪರಿವರ್ತಿತ ಜಮೀನನ್ನು Layout - Residential ಉದ್ದೇಶಕ್ಕಾಗಿ ಮಾತ್ರ ಉಪಯೋಗಿಸಿಕೊಳ್ಳತಕ್ಕದ್ದು. ಬೇರೆ ಉದ್ದೇಶಕ್ಕಾಗಿ ಉಪಯೋಗಿಸಬೇಕಾದರೆ ಸೆಕ್ಷನ್ 97 ರ ಪ್ರಕಾರ ಮರು ಅನುಮತಿಯನ್ನು ಪಡೆಯತಕ್ಕದ್ದು. ಸದರಿ ಭೂ ಪರಿವರ್ತಿತ ಜಮೀನನ್ನು ಯಾವ ಉದ್ದೇಶಕ್ಕಾಗಿ ಉಪಯೋಗಿಸಬೇಕಾದರೆ ಸೆಕ್ಷನ್ 97 ರ ಪ್ರಕಾರ ಮರು ಅನುಮತಿಯನ್ನು ಪಡೆಯತಕ್ಕದ್ದು. ಸದರಿ ಭೂ ಪರಿವರ್ತಿತ ಜಮೀನನ್ನು ಯಾವ ಉದ್ದೇಶಕ್ಕಾಗಿ ಉಪಯೋಗಿಸಬೇಕಾದರೆ ಆ ಉದ್ದೇಶಕ್ಕಾಗಿ ಯೋಜನಾ ಪ್ರಾಧಿಕಾರ / ಅಭಿವೃದ್ಧಿ ಮಂಡಳಿ / ಸಿಎಂಸಿ / ಟಿಎಂಸಿ / ಮಾಲೀಕ, ನಿಯಂತ್ರಣ ಉದ್ದೇಶಕ್ಕಾಗಿ ಪರಿವರ್ತನೆಯಾದಿದರೇ ಆ ಉದ್ದೇಶಕ್ಕಾಗಿ ಯೋಜನಾ ಪ್ರಾಧಿಕಾರ / ಅಭಿವೃದ್ಧಿ ಮಂಡಳಿ / ಸಿಎಂಸಿ / ಟಿಎಂಸಿ / ಮಾಲೀಕ, ನಿಯಂತ್ರಣ ಮಂಡಳಿ / ಗ್ರಾಮ ಪಂಚಾಯಿತಿಗಳಿಂದ ಅಗತ್ಯ ಮಂಜೂರಾತಿಯನ್ನು ಪಡೆಯತಕ್ಕದ್ದು.

3. ಸದರಿ ಭೂಪರಿವರ್ತನೆ ಆದೇಶವನ್ನು ಅರ್ಜಿದಾರರು ನೀಡಿರುವ ಅಫಿಡವಿಟ್ (ಪ್ರಮಾಣಪತ್ರ) ಆಧಾರದಲ್ಲಿ ನೀಡಲಾಗಿದ್ದು, ಅಫಿಡವಿಟ್ ಪ್ರಮಾಣಪತ್ರದಲ್ಲಿ ನೀಡಿರುವ ಮಾಹಿತಿಯು ಒಂದು ವೇಳೆ ತಪ್ಪಾಗಿದ್ದಲ್ಲಿ, ಈ ಆದೇಶವು ಎಯಿಮಾನುಸಾರ ರದ್ದು ಮಾಡುವ ಹಕ್ಕನ್ನು ಒಳಪಡುತ್ತದೆ.

4. ಸರ್ಕಾರ ಯೋಜನಾ ಪ್ರಾಧಿಕಾರ/ಗ್ರಾಮ ಪಂಚಾಯಿತಿ/ಅಭಿವೃದ್ಧಿ ಪ್ರಾಧಿಕಾರ/ಸ್ಥಳೀಯ ಪ್ರಾಧಿಕಾರವು ಲೇ ಔಟ್ ಪ್ಲಾನ್ ಗೆ ಅನುಮೋದನೆ ನೀಡುವವರೆಗೆ ಮಾತ್ರವೇ ಕಂದಾಯ ಇಲಾಖೆಯ ಭೂಮಿ ಪಂಚಾಂಶದಲ್ಲಿ ನಿರ್ವಹಿಸಿ, ಕಾಲೋನಿ ತೆಗೆಳಿಸುತ್ತಿರುವ ಪಹಣಿಯಲ್ಲಿರುವ ಭೂ ಪರಿವರ್ತನೆಯಾಗಿರುವ ಕ್ಷೇತ್ರದ ಪೂರ್ಣ ವಿಸ್ತೀರ್ಣವನ್ನು ವಿಭಜನೆ ಮಾಡದೇ ಒಂದೇ ಘಟಕವನ್ನಾಗಿ ಮಾರಾಟ ಮಾಡಬಹುದಾಗಿದೆ. ಸರ್ಕಾರ ಯೋಜನಾ ಪ್ರಾಧಿಕಾರ ಅಥವಾ ಗ್ರಾಮ ಪಂಚಾಯಿತಿ ಅಥವಾ ಸಂಬಂಧಿಸಿದ ಸ್ಥಳೀಯ ಪ್ರಾಧಿಕಾರವು ಲೇ ಔಟ್ ಪ್ಲಾನ್ ಗೆ ಅನುಮೋದನೆ ನೀಡಿದ ನಂತರ ಭೂ ಪರಿವರ್ತನೆಯಾಗಿರುವ ಕ್ಷೇತ್ರದಲ್ಲಿ ಸಾರ್ವಜನಿಕ ಉದ್ದೇಶಕ್ಕೆ, ಮೀಸಲಿರಿಸಿದ ವಿಸ್ತೀರ್ಣವನ್ನು ಬಿಟ್ಟು, ಉಳಿದ ವಿಭಜಿತ ಕ್ಷೇತ್ರವನ್ನು, ಆಯಾ ಕ್ಷೇತ್ರಕ್ಕೆ ನೀಡಿರುವ ಆಸ್ತಿಯ ಗುರುತಿನ ಸಂಖ್ಯೆ (Property id) ಮೇರೆಗೆ ಮಾರಾಟ ಮಾಡಬಹುದಾಗಿರುತ್ತದೆ.

ಷರತ್ತುಗಳ ವಿವರ

ಬಾಗಲಕೋಟೆ ಜಿಲ್ಲೆ, ಮುಧೋಳ ತಾಲ್ಲೂಕು ಮುಧೋಳ ಹೋಬಳಿ, ಮುಧೋಳ ಗ್ರಾಮದ 504/*/2ಎ/1 , ಸ.ನಂ. ರಲ್ಲಿನ ಒಟ್ಟು 1.14.0.00 ಎಕರೆ/ಗುಂಟೆ ವಿಸ್ತೀರ್ಣದಲ್ಲಿ 1.14.0.00 ಎಕರೆ/ಗುಂಟೆ ವಿಸ್ತೀರ್ಣದ ಭೂ ಪರಿವರ್ತಿತ ಜಮೀನಿಗೆ ಚೌಕುಬಂದಿ:

ಸ.ನಂ	ವಿಸ್ತೀರ್ಣ		ಚೌಕುಬಂದಿ			
	ಒಟ್ಟು ವಿಸ್ತೀರ್ಣ	ಭೂಪರಿವರ್ತಿತ ವಿಸ್ತೀರ್ಣ	ಪೂರ್ವಕ್ಕೆ,	ಪಶ್ಚಿಮಕ್ಕೆ,	ಉತ್ತರಕ್ಕೆ,	ದಕ್ಷಿಣಕ್ಕೆ,
504/*/2ಎ/1	1.14.0.00	1.14.0.00	ಲಾ.ಗು.ಹಿ.ಸ.ನಂ-2ಎ/2	ಲಾ.ಗು.ರಿ.ಸ.ನಂ-503	ಲಾ.ಗು.ಹಿ.ಸ.ನಂ-1ಎ	ಲಾ.ಗು.ರಿ.ಸ.ನಂ-512

ಸಹಿ
ಜಿಲ್ಲಾಧಿಕಾರಿಗಳು
ಬಾಗಲಕೋಟೆ ಜಿಲ್ಲೆ.

KONANUR MALLAIAH JANAKI

ಪ್ರತಿಯನ್ನು ಮುಂದಿನ ಸೂಕ್ತ ಕ್ರಮಕ್ಕಾಗಿ ಕಳಕಂಡವರಿಗೆ ಕಳುಹಿಸಿದೆ :

1.ತಹಶೀಲ್ದಾರ್ ಮುಧೋಳ ರವರಿಗೆ ಮೂಲ ಕಡತ ಹಾಗೂ ಚಲನ್ ಸಮೇತ ಕಳುಹಿಸುತ್ತಾ, ಈ ಆದೇಶದ ಪ್ರಕಾರ ಸಂಬಂಧಪಟ್ಟ ಸರ್ವೆ ನಂಬರ್ ಭೂ ಪರಿವರ್ತನೆಯಾಗಿದೆ ಎಂದು ಸಂಬಂಧಪಟ್ಟ ಆರ್.ಟಿ.ಸಿ ಯಲ್ಲಿ ನಮೂದಿಸತಕ್ಕದ್ದು, ಮತ್ತು ಈ ಜಮೀನಿಗೆ ಖಾತೆದಾರರ ಲೆಕ್ಕದಲ್ಲಿ ಸದರಿ ಜಮೀನಿನ ಭೂ ಕಂದಾಯವನ್ನು ಕಡಿಮೆಗೊಳಿಸುವುದು.

2.Madhol (ಪ್ರಾಧಿಕಾರ / ನಗರಪಾಲಿಕೆ) ಇವರಿಗೆ ಮುಂದಿನ ಸೂಕ್ತ ಕ್ರಮಕ್ಕಾಗಿ.

3.ಉಪ ವಿಭಾಗಾಧಿಕಾರಿಗಳು,ಬಾಗಲಕೋಟೆಯವ ವಿಭಾಗ ರವರಿಗೆ.

4.ಉಪ ನಿರ್ದೇಶಕರು, ಭೂಮಾಪನ ಮತ್ತು ಭೂದಾಖಲೆಗಳ ಬಾಗಲಕೋಟೆಯವ ವಿಭಾಗ.

5.ಅರ್ಜಿದಾರರಾದ ಶ್ರೀ/ಶ್ರೀಮತಿ: ಸುರೇಶ ಬಸಪ್ಪ, ಮುಳ್ಳೂರ ಬೆನ್ ಬಸಪ್ಪ , ವಿಳಾಸ: ಮುಧೋಳ; ರವರಿಗೆ ದೃಢೀಕೃತ ಅಂಚೆ ಮೂಲಕ.

6.ಹೆಚ್ಚಿನ ಪ್ರತಿ.

(3) KJ p

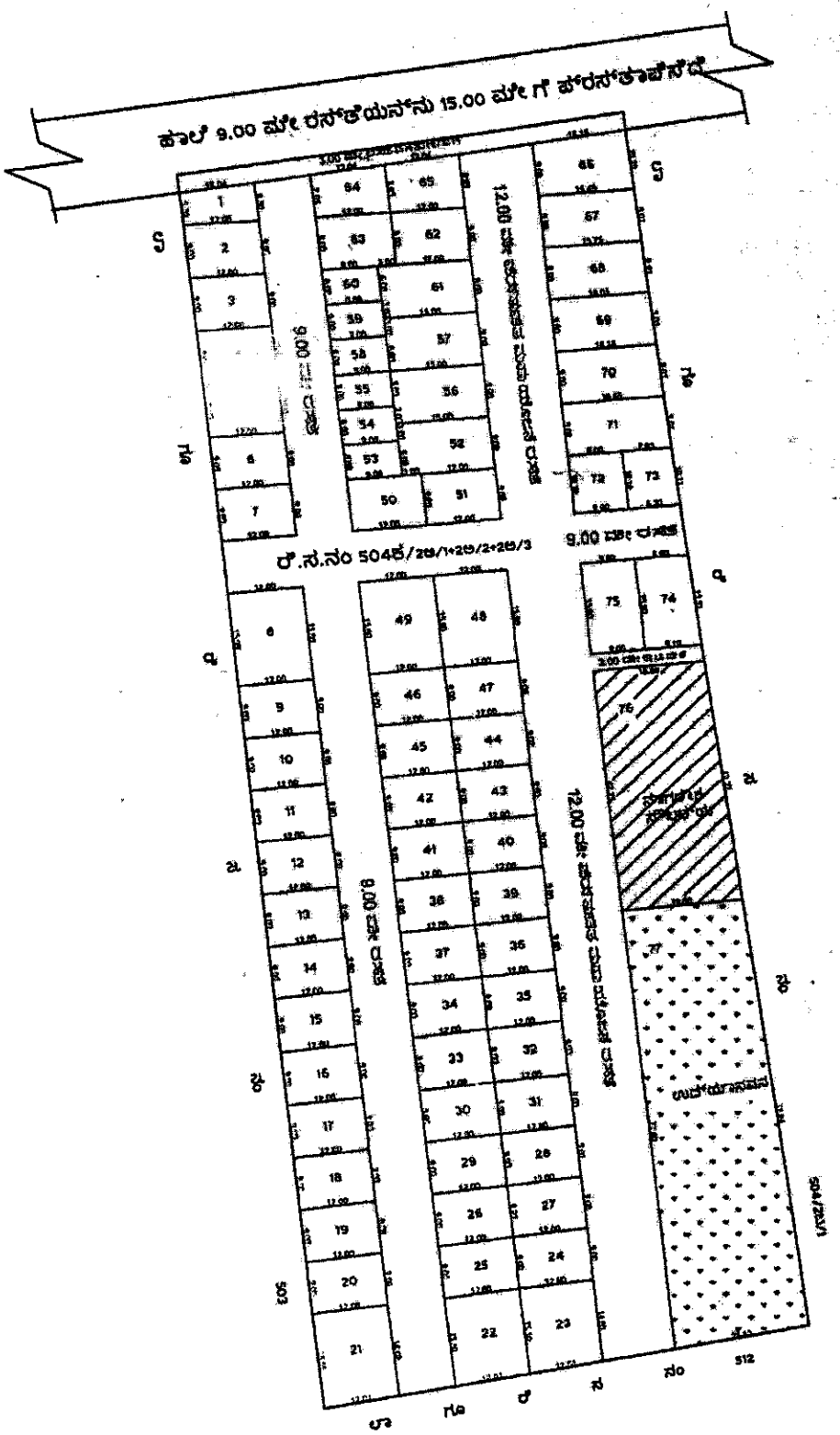
ಹಾಲೆ 9.00 ಮೀ ರಸ್ತೆಯನ್ನು 15.00 ಮೀ ಗೆ ಪರಿವರ್ತಿಸಿದೆ
ರೆ.ಸ.ನಂ 504ಪಿ/2ಬಿ/1+2ಬಿ/2+2ಬಿ/3
9.00 ಮೀ ರಸ್ತೆ
12.00 ಮೀ ಅಗಲದ ಮಾರ್ಗದ ರಸ್ತೆ
ಉದ್ಯಾನವನ
504/2ಬಿ/1

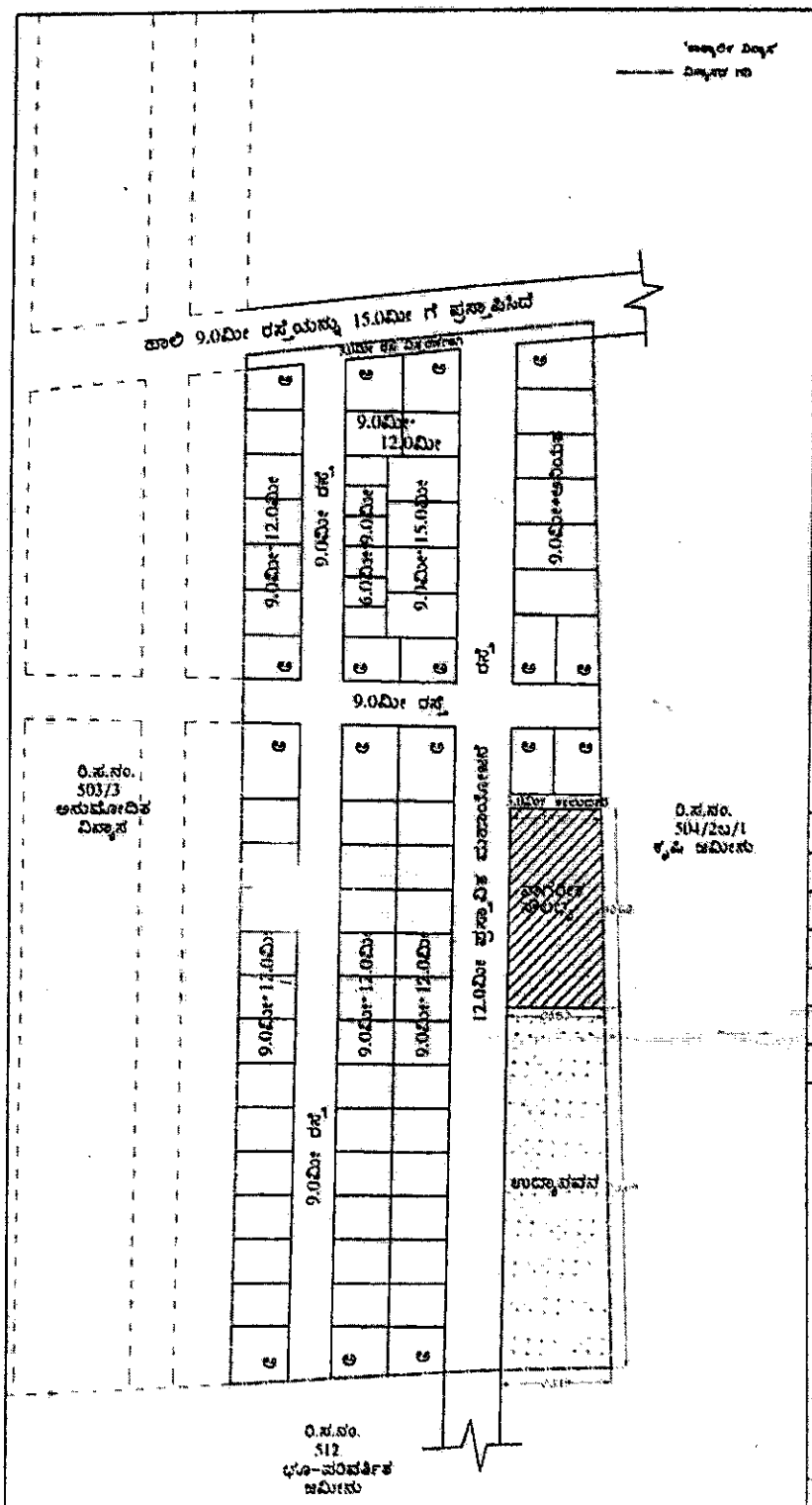

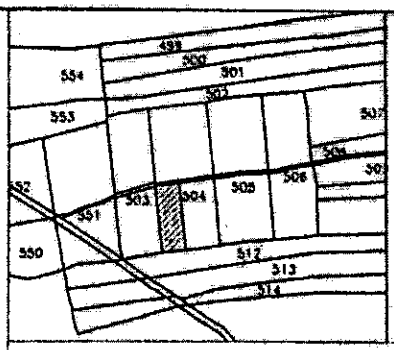

ವಸತಿಗಾಗಿ ಭೂ-ಉಪಯೋಗ ವಿಶ್ಲೇಷಣೆ

ಕ್ರ.ಸಂ	ಭೂ ಉಪಯೋಗ	ವಿಸ್ತೀರ್ಣ ಚ.ಮೀ	ಶೇಕಡಾವಾರು
1	ವಸತಿಗಾಗಿ	8555.18	52.85
2	ಉದ್ಯಾನವನ	1619.24	10.00
3	ನಾಗರೀಕ ಸೌಲಭ್ಯ	810.74	05.01
4	ರಸ್ತೆಗಾಗಿ	5202.28	32.14
	ಒಟ್ಟು	16187.44	100.00

ವಸತಿ ನಿವೇಶನಗಳ ವಿವರ

ಕ್ರ.ಸಂ	ನಿವೇಶನಗಳ ಅಳತೆ	ಸಂಖ್ಯೆ
1.	6.0ಮೀ * 9.0ಮೀ.	06
2.	9.0ಮೀ * 12.0ಮೀ.	43
3.	9.0ಮೀ * 15.0ಮೀ.	04
4.	9.0ಮೀ * ಅನಿಯತ	05
5.	ಅನಿಯತ	17
		ಒಟ್ಟು: 75

NORTH

ಅಳತೆ:1:1000

ಕರ್ನಾಟಕ ಸರ್ಕಾರ

ನಗರ ಯೋಜನಾ ಪ್ರಾಧಿಕಾರ, ಮುಧೋಳ

ಸದಸ್ಯ ಕಾರ್ಯದರ್ಶಿ,
ನಗರ ಯೋಜನಾ ಪ್ರಾಧಿಕಾರ,
ಮುಧೋಳ

ಸೂಚನೆ:

1)ಮಾನ್ಯ ಜಿಲ್ಲಾಧಿಕಾರಿಗಳು, ಬಾಗಲಕೋಟೆ ಇವರ ಅಧಿಕೃತ ಜ್ಞಾಪನೆ ಪತ್ರ ಸಂಖ್ಯೆ:586472, 586474, 586473, ದಿನಾಂಕ:-30-01-2024 ರನ್ವಯ ವಸತಿ ಉದ್ದೇಶಕ್ಕಾಗಿ ಭೂ-ಪರಿವರ್ತನೆಯಾಗಿರುತ್ತದೆ.

2)ಸದರಿ ಕಾಲ್ಪನಿಕ ವಿನ್ಯಾಸಕ್ಕೆ, ಸ್ಥಳದಲ್ಲಿ ಗುರುತಿಸಿ ಅಭಿವೃದ್ಧಿಪಡಿಸಲು ಮಾತ್ರ ಅನುಮೋದನೆ ನೀಡಲಾಗಿದ್ದು ನಿವೇಶನಗಳ ಸೋಂದರ್ಭಗಳ ಬಳಸುವಂತಿಲ್ಲ.

3)ಸದರಿ ವಿನ್ಯಾಸವನ್ನು ಸಂಪೂರ್ಣ ಅಭಿವೃದ್ಧಿ ಪಡಿಸಿ ಅಂತಿಮ ಅನುಮೋದನೆ ಪಡೆಯತಕ್ಕದ್ದು.

4) ಸದರಿ ವಿನ್ಯಾಸವನ್ನು ಭೂ-ದಾಖಲೆಗಳ ಸಹಾಯಕ ನಿರ್ದೇಶಕರು, ಬಾಗಲಕೋಟೆ ಕಛೇರಿಯ ಪಿಟ್ ಶೀಟ್ ಆಧರಿಸಿ ಸಿದ್ಧಪಡಿಸಲಾಗಿದೆ.

5) ಈ ಕಾರ್ಯಾಲಯದ ಆದೇಶ ಪತ್ರ ಸಂಖ್ಯೆ:-ನಯೋಪ್ರಾಮು/ವಿನ್ಯಾಸ/2023-24/ ದಿನಾಂಕ:- -03-2024 ರಲ್ಲಿನ ನಿಬಂಧನೆಗಳಿಗೆ ಒಳಪಟ್ಟು ತಾತ್ಕಾಲಿಕ ವಿನ್ಯಾಸ ನಕ್ಷೆ ಅನುಮೋದಿಸಲಾಗಿದೆ.

ಬಾಗಲಕೋಟೆ ಜಿಲ್ಲೆ ಮುಧೋಳ ತಾಲ್ಲೂಕು ಮುಧೋಳ ಗ್ರಾಮದ ಪ್ರ.ಸ.ನಂ.504+/2ಅ/1 ಕ್ಷೇತ್ರ: 0ಎ-14ಗು0, ಪ್ರ.ಸ.ನಂ.504+/2ಅ/2 ಕ್ಷೇತ್ರ: 0ಎ-12ಗು0 ಮತ್ತು ಪ್ರ.ಸ.ನಂ.504+/2ಅ/3 ಕ್ಷೇತ್ರ: 0ಎ-12ಗು0 ಒಟ್ಟು ಕ್ಷೇತ್ರ 04ಎ-00ಗು0 ಜಮೀನಿಗೆ ವಸತಿ ಉದ್ದೇಶಕ್ಕಾಗಿ ತಿಳಿಯಪಡಿಸಿದ ತಾತ್ಕಾಲಿಕ ವಿನ್ಯಾಸದ ನಕ್ಷೆ.

ಅಳತೆ:1:1000

ಪ್ರ.ಸಂಖ್ಯೆ: /21-24

स्थायी लेखा संख्या कार्ड

Permanent Account Number Card

CBIPG5561M

नाम /Name

CHETANKUMAR SANGAPPA GANI

पिता का नाम /Father's Name

SANGAPPA GANI

जन्म की तारीख /Date of Birth

20/07/1997

हस्ताक्षर /Signature

Building

(6)

ಮುಧೋಳ್ ನಗರಸಭೆ

ಕಟ್ಟಡ ಪರವಾನಿಗೆ

ಕರ್ನಾಟಕ ಪೌರಸಭೆಗಳ ಅಧಿನಿಯಮ-1964ರ ಕಲಂ 187 ಹಾಗೂ ಕರ್ನಾಟಕ ನಗರ ಮತ್ತು ಗ್ರಾಮಾಂತರ ಯೋಜನಾ ಕಾಯ್ದೆ-1961ರ ಕಲಂ 15ರ ಅನ್ವಯ

ಸಂಖ್ಯೆ : **MDL-LBPAS-11857/25-26/BP** ದಿನಾಂಕ : **10 Nov 2025**

ಅರ್ಜಿ ಸಂಖ್ಯೆ:MDL-LBPAS-11857/25-26/BP, ದಿನಾಂಕ: 27 Oct 2025 ರಂದು ಶ್ರೀಮತಿ/ಶ್ರೀ SIDDU URF SIDDAPPA SADASHIV BATAKURKI ರವರು ನೀಡಿದ ಅರ್ಜಿಯನ್ನು ಪರಿಶೀಲಿಸಲಾಯಿತು, ಅದಕ್ಕೆ ಲಗತ್ತಿಸಲಾಗಿರುವ ನಕ್ಷೆಯನ್ನು ಅನುಸರಿಸಿ Mudhol City Municipal Council ವ್ಯಾಪ್ತಿಯ ಕಂದಾಯ ವಸೂಲಾತಿ ಏರಿಯಾ ಸಂಖ್ಯೆ:14 . (ಪ್ರಸ್ತುತ ಚುನಾವಣಾ ವಾರ್ಡ್ ಸಂಖ್ಯೆ:15), Bagalkot ,15 ಪ್ರದೇಶದಲ್ಲಿರುವ ಗ್ರಾಮದ ರೆವಿನ್ಯೂ ಸರ್ವೇ ನಂಬರ್: 504/K , ನಿವೇಶನದ ಸಂಖ್ಯೆ 14 ., ಅಸೆಸ್‌ಮೆಂಟ್ / ಖಾತೆ / ಡೋರ್ ನಂಬರ್ 3655514, ಶ್ರೀಮತಿ/ಶ್ರೀ SIDDU URF SIDDAPPA SADASHIV BATAKURKI GULGALJAMBAGI, SURESH BASAPPA MULLUR MUDHOL, YAMANAPPA RAMAPPA KOLI JIRAGAL ಇವರ ಮಾಲೀಕತ್ವದ ಸ್ವತ್ತಿನಲ್ಲಿ ಈ ಕೆಳಗೆ ಕಾಣಿಸಿದ ಷರತ್ತುಗಳು ಹಾಗೂ ನಿಬಂಧನೆಗಳಿಗೊಳಪಟ್ಟು ವಸತಿ ಉದ್ದೇಶಕ್ಕೆ ಕಟ್ಟಡ ನಿರ್ಮಾಣ ಮಾಡಲು ಪರವಾನಿಗೆ ಮಂಜೂರು ಮಾಡಲಾಗಿದೆ.

ಮಂಜೂರಾದ ಪರವಾನಿಗೆ ವಿವರಗಳು :

- ಕಟ್ಟಡವನ್ನು ಜಾಗದ ಎಡ ಭಾಗದಲ್ಲಿ 1.00 ಮೀ., ಬಲ ಭಾಗದಲ್ಲಿ 1.00 ಮೀ., ಹಿಂಭಾಗದಲ್ಲಿ 1.00 ಮೀ., ಮುಂಭಾಗದಲ್ಲಿ 1.50 ಮೀ., ಜಾಗವನ್ನು ಬಿಟ್ಟು ಕಟ್ಟಿಕೊಳ್ಳಬೇಕು.
  ನಿವೇಶನದ ವಿಸ್ತೀರ್ಣ :108.00 ಚ.ಮೀ., ಎಫ್.ಎ.ಆರ್ : 0.62

  ಚೆಕ್ ಬಂದಿ :-

  ಪೂರ್ವಕ್ಕೆ :PLOT ROAD

  ಪಶ್ಚಿಮಕ್ಕೆ :RTC NO:503

  ಉತ್ತರಕ್ಕೆ :PLOT NO:12

  ದಕ್ಷಿಣಕ್ಕೆ :PLOT NO:14

ಮಹಡಿಯ ಸಂಖ್ಯೆ	ಮಹಡಿಯ ಉಪಯೋಗ	ಒಟ್ಟು ವಿಸ್ತೀರ್ಣ (ಚದರ ಮೀಟರ್)	ಒಟ್ಟು ಕಡಿತಗೊಳಿಸಿದ ವಿಸ್ತೀರ್ಣ (ಚದರ ಮೀಟರ್)	ನಿರ್ಮಿಸಿದ ವಿಸ್ತೀರ್ಣ (ಚದರ ಮೀಟರ್)	ನಿವ್ವಳ ಕಡಿತಗೊಳಿಸಿದ ವಿಸ್ತೀರ್ಣ (ಚದರ ಮೀಟರ್)	FAR ವಿಸ್ತೀರ್ಣ (ಚದರ ಮೀಟರ್)
GROUND FLOOR	ವಸತಿ	66.5	0	66.5	0	66.5
ROOF	ಚಾವಣಿ	0	0	0	0	0
	ಮೊತ್ತ	**66.5**	**0**	**66.5**	**0**	**66.5**

- ನಿರಾಕ್ಷೇಪಣಾ ಪ್ರಮಾಣಪತ್ರಗಳು :
- ದಾಖಲೆಯಲ್ಲಿರುವಂತೆ ಕಟ್ಟಡದ ನಕ್ಷೆ ತಯಾರಿಸಿದ ವೃತ್ತಿಪರರ ಹೆಸರು ಮತ್ತು ವಿಳಾಸ : ALLABAKSH GAIBUSAB MOMIN,NEAR TEACHERS COLONY WARD NO 5 MUDHOL, KARNATAKA, BAGALKOT, 587313
- ದಾಖಲೆಯಲ್ಲಿರುವಂತೆ ಮೇಲ್ವಿಚಾರಣೆ ಮಾಡುವ ವೃತ್ತಿಪರರ ಹೆಸರು ಮತ್ತು ವಿಳಾಸ : ALLABAKSH GAIBUSAB MOMIN,NEAR TEACHERS COLONY WARD NO 5 MUDHOL, KARNATAKA, BAGALKOT, 587313
- ಪಾವತಿಯಾದ ಒಟ್ಟು ಶುಲ್ಕ ರೂ. 19857.00 ರಶೀದಿ ನಂ. KBPAS/RecptNo/257642/25-26 ದಿನಾಂಕ: 10 Nov 2025

  ಶುಲ್ಕಗಳ ಮಾಹಿತಿ: Construction fees ರೂ. 5625.00, Slum Fees ರೂ. 250.00, Storage Fees ರೂ. 2000.00, 1% Labour Cess ರೂ. 11982.00
- ಪರವಾನಿಗೆಯು ಚಾಲ್ತಿಯಲ್ಲಿರುವ ಅವಧಿ 10/11/2025 ರಿಂದ 09/11/2026 ರವರೆಗೆ ಮಾತ್ರ

ಷರತ್ತುಗಳು:

1. ಮಂಜೂರಾದ ನಕಾಶೆಯಂತೆ ಕಟ್ಟಡವನ್ನು ಕಟ್ಟತಕ್ಕದ್ದು.
2. ಮಂಜೂರಾದ ನಕಾಶೆಗೆ ಹೊರತಾಗಿ ಬೇರೆ ಯಾವುದೇ ಅನಧಿಕೃತ ಕಟ್ಟಡ ಕೆಲಸವನ್ನು ಮಾಡತಕ್ಕದ್ದಲ್ಲ.
3. ಕಟ್ಟಡದ ಕಾಮಗಾರಿಗಳು ಪರವಾನಿಗೆ ಅವಧಿಯೊಳಗೆ ಪೂರ್ತಿಯಾಗದಿದ್ದಲ್ಲಿ, ನಿಯಮಾನುಸಾರ ಈ ಕಛೇರಿಗೆ ಸೂಕ್ತ ಅರ್ಜಿ ಸಲ್ಲಿಸಿ, ಶುಲ್ಕ ಪಾವತಿಸಿ ಪರವಾನಿಗೆಯನ್ನು ನವೀಕರಿಸಿಕೊಳ್ಳತಕ್ಕದ್ದು.
4. ಕಟ್ಟಡದ ಕೆಲಸ ಪೂರ್ತಿಯಾದ ಕೂಡಲೇ ಅದರಲ್ಲಿ ವಾಸಿಸುವ/ಕಟ್ಟಡವನ್ನು ಉಪಯೋಗಿಸುವ ಮುಂಚಿತವಾಗಿ ನಿಯಮಾನುಸಾರ ಪ್ರಕಾರ ಕಾಮಗಾರಿ ಪೂರ್ಣಗೊಂಡ ಬಗ್ಗೆ ಈ ಕಛೇರಿಗೆ ಅರ್ಜಿ ಸಲ್ಲಿಸಿ ವಾಸ್ತವ್ಯ ಉಪಯೋಗದ ಬಗ್ಗೆ ದೃಢೀಕರಣ ಪತ್ರ ಪಡೆದುಕೊಳ್ಳತಕ್ಕದ್ದು.
5. ಆರ್.ಸಿ.ಸಿ, ಹೆಂಚು ಮಾಡಿನಿಂದ ಮಳೆ ನೀರು ಭೂಮಿಗೆ ಹರಿದು ಹೋಗಲು ಯೋಗ್ಯ ರೀತಿಯಲ್ಲಿ ನಳಿಗೆ (ಪೈಪು) ಜೋಡಣೆ ಮಾಡತಕ್ಕದ್ದು.
6. ಸ್ಥಳ ತನಿಖೆ ವೇಳೆ ನಿವೇಶನದ ಗಡಿ ಅಳತೆಯಲ್ಲಿ ಕಂಡು ಬಂದಿರುವ ವ್ಯತ್ಯಾಸಗಳನ್ನು ಸ್ಥಳ ನಕಾಶೆಯಲ್ಲಿ ಮಾಡಿದ ಎಲ್ಲಾ ತಿದ್ದುಪಡಿಗಳನ್ನು ಪಾಲಿಸಲು ಪರವಾನಿಗೆದಾರರು ಬದ್ಧರಿರತಕ್ಕದ್ದು.
7. ಸ್ಥಳೀಯ ಸ್ಥಳಿಯ ರಸ್ತೆ ಬದಿಗಳಲ್ಲಿ ಪ್ರಸ್ತಾಪಿತ ಕಟ್ಟಡ ನಿರ್ಮಾಣದ ಬಗ್ಗೆ ಸಾಮಾಗ್ರಿ ಇತ್ಯಾದಿ ದಾಸ್ತಾನು ಮಾಡತಕ್ಕದ್ದಲ್ಲ.
8. ನಿಯಮಾನುಸಾರ ಪರವಾನಿಗೆ ಪಡೆದ ಅವಧಿಯೊಳಗೆ ಕಟ್ಟಡ ಕಾಮಗಾರಿ ಮಾಡತಕ್ಕದ್ದು. ತಪ್ಪಿದ್ದಲ್ಲಿ ಹೊಸ ಪರವಾನಿಗೆ ಪಡೆಯತಕ್ಕದ್ದು.
9. ಯೋಜಿತ ಕಟ್ಟಡದ ತಳಪಾಯ ಸೂಪರ್ ಸ್ಟ್ರಕ್ಚರ್ ಮತ್ತು ಉಳಿದ ಕಾಮಗಾರಿಗಳ ಪ್ರತಿ ಹಂತದಲ್ಲಿ ಈ ಕಛೇರಿಗೆ ಮುಂಚಿತವಾಗಿ ಲಿಖಿತವಾಗಿ ತಿಳಿಸಿ,

   ಅ) ಕಟ್ಟಡದ ತಳಪಾಯದ ಅಗೆತ ಪೂರ್ಣಗೊಂಡ ನಂತರ
   ಆ) ಕಟ್ಟಡದ ಬೇಸ್‌ಮೆಂಟ್ ಹಂತ ಪೂರ್ಣಗೊಂಡ ನಂತರ
   ಇ) ಭೂಮಟ್ಟದಿಂದ ಮೇಲಿನ ಕಟ್ಟಡದ ಭಾಗ ಪೂರ್ಣಗೊಂಡ ನಂತರ ಹಾಗೂ
   ಈ) ಮುಕ್ತಾಯ ಪ್ರಮಾಣ ಪತ್ರ ನೀಡುವ ಪೂರ್ವದಲ್ಲಿ ನಿರ್ಮಾಣ ಕಾರ್ಯವು ಕಾನೂನು ಮತ್ತು ಬೈಲಾಗಳಿಗೆ ವ್ಯತಿರಿಕ್ತವಾಗಿರುವುದಿಲ್ಲವೆಂದು

   ಸಹಾಯಕ ಕಾರ್ಯಪಾಲಕ ಅಭಿಯಂತರರು/ಸಹಾಯಕ ಅಭಿಯಂತರರು/ಕಿರಿಯ ಅಭಿಯಂತರರು ಖಚಿತ ಪಡಿಸಿದ ನಂತರ ಕಾಮಗಾರಿಯನ್ನು ಮುಂದುವರಿಸತಕ್ಕದ್ದು ಹಾಗೂ ಕಟ್ಟಡ ಮಾಲೀಕರು ಮತ್ತು ಕಟ್ಟಡ ನಿರ್ಮಾಣ ಇಂಜಿನಿಯರ್ ರವರು ಈ ಕಛೇರಿಗೆ ನಿರ್ಮಾಣವು ಪರವಾನಿಗೆ ರೀತ್ಯಾ ಇರುವುದಾಗಿ ದೃಢೀಕರಣ ಪತ್ರ ಸಲ್ಲಿಸತಕ್ಕದ್ದು.
10. ಸಾರ್ವಜನಿಕ ದಾರಿ ಹಾಗೂ ಮಳೆ ನೀರು, ಹರಿಯುವ ರಾಜಕಾಲುವೆಗೆ ಅಡ್ಡಿ ಉಂಟು ಮಾಡತಕ್ಕದ್ದಲ್ಲ.
11. ಕಟ್ಟಡದಲ್ಲಿ ಕಡ್ಡಾಯವಾಗಿ ಮಳೆ ನೀರು ಕೊಯ್ಲಿನ ವಿಧಾನವನ್ನು ಅಳವಡಿಸತಕ್ಕದ್ದು.
12. ಕಟ್ಟಡದ ನಿರ್ಮಾಣದ ಸ್ಥಳದಲ್ಲಿ ಪರಿಸರ ಮಾಲಿನ್ಯ ಉಂಟಾದಲ್ಲಿ ಪರವಾನಿಗೆದಾರರೇ ಜವಾಬ್ದಾರರು.
13. ಕಟ್ಟಡ ಕಾಮಗಾರಿಗೆ ಬಾಲ ಕಾರ್ಮಿಕರನ್ನು ನೇಮಿಸತಕ್ಕದ್ದಲ್ಲ.
14. ಕಟ್ಟಡದ ತಳಪಾಯ ಭೂಕಂಪನವನ್ನು ತಡೆಗಟ್ಟುವ ರೀತಿಯಲ್ಲಿ ನ್ಯಾಷನಲ್ ಬಿಲ್ಡಿಂಗ್ ಕೋಡ್ ಮತ್ತು IS 93-2000 ರನ್ವಯ ನಿರ್ಮಿಸತಕ್ಕದ್ದು
15. ಕಟ್ಟಡ ನಿರ್ಮಾಣ ಹಂತದಲ್ಲಿ ಪಕ್ಕದ ನಿವೇಶನದ ಆಸ್ತಿಗಳಿಗೆ ಹಾನಿಯಾದಲ್ಲಿ ಕಟ್ಟಡದ ಮಾಲೀಕರೇ ಜವಾಬ್ದಾರರು.
16. ಕಟ್ಟಡದ ಶೌಚಾಲಯದ ಹೊಂಡವನ್ನು ಸುತ್ತಲಿನ ಬಾವಿಯಿಂದ 18 ಮೀ. ಅಂತರದಲ್ಲಿ ನಿರ್ಮಿಸತಕ್ಕದ್ದು.
17. ಕಟ್ಟಡದ ಘನತ್ಯಾಜ್ಯವನ್ನು ಕಟ್ಟಡದ ಮಾಲೀಕರು ಸ್ವಂತ ವೆಚ್ಚದಲ್ಲಿ ವಿಲೇಗೆ ವ್ಯವಸ್ಥೆ ಕಲ್ಪಿಸತಕ್ಕದ್ದು.
18. ಕಟ್ಟಡದ ಒಳಚರಂಡಿ ಸಂಪರ್ಕವನ್ನು ಈ ಕಛೇರಿಯ ಪೂರ್ವಾನುಮತಿ ಪಡೆದು ಸಂಪರ್ಕಿಸತಕ್ಕದ್ದು.
19. ಈ ಪರವಾನಿಗೆಯನ್ನು ಕಟ್ಟಡಕ್ಕೆ ತಾತ್ಕಾಲಿಕ ವಿದ್ಯುತ್ ಸಂಪರ್ಕಕ್ಕೆ ಮಾತ್ರ ಪರಿಗಣಿಸುವುದು.
20. ಅನುಮೋದಿತ ನಕ್ಷೆಯ ಪ್ರತಿಯನ್ನು 3 ಅಡಿ ಅಗಲ x 2 ಅಡಿ ಎತ್ತರದ ಫಲಕ ಸಿದ್ಧಪಡಿಸಿ ಕಟ್ಟಡದ ಕಾಮಗಾರಿ ಪ್ರಾರಂಭದಿಂದ ಪೂರ್ಣಗೊಳ್ಳುವ ಸಂಪೂರ್ಣ ಅವಧಿಗೆ ಕಟ್ಟಡದ ಮುಂಭಾಗದಲ್ಲಿ ಕಡ್ಡಾಯವಾಗಿ ಸಾರ್ವಜನಿಕರಿಗೆ ಕಾಣುವಂತೆ ಅಳವಡಿಸತಕ್ಕದ್ದು.
21. ಮೇಲ್ಕಂಡ ಆದೇಶವನ್ನು ಉಲ್ಲಂಘಿಸಿದಲ್ಲಿ ಕಟ್ಟಡದ ಕಾಮಗಾರಿಯನ್ನು ಮುಂದಿನ ಆದೇಶದವರೆಗೆ ನಿಲ್ಲಿಸಲಾಗುವುದು.
22. ನ್ಯಾಯಾಲಯದಲ್ಲಿ ಆಸ್ತಿಗೆ ಸಂಬಂಧಪಟ್ಟಂತೆ ಯಾವುದೇ ವ್ಯಾಜ್ಯವಿದ್ದ ಸಂದರ್ಭದಲ್ಲಿ ನ್ಯಾಯಾಲಯದ ಆದೇಶದನ್ವಯ ನಗರ ಸ್ಥಳೀಯ ಸಂಸ್ಥೆ ತೆಗೆದುಕೊಳ್ಳುವ ತೀರ್ಮಾನಕ್ಕೆ ಬದ್ಧರಾಗತಕ್ಕದ್ದು ಹಾಗೂ ಈ ಕುರಿತು ಯಾವುದೇ ಆರ್ಥಿಕ ನಷ್ಟವಾದಲ್ಲಿ ಅದಕ್ಕೆ ನಗರ ಸ್ಥಳೀಯ ಸಂಸ್ಥೆಯು ಹೊಣೆಯಾಗಲಾರದು.
23. ಕಟ್ಟಡ ಪರವಾನಿಗೆ ಪಡೆದ ನಂತರ ಶುಲ್ಕ ಸಂದಾಯದ ಕುರಿತು ಲೆಕ್ಕ ಪರಿಶೋಧಕರಿಂದ ಯಾವುದೇ ತರಹದ ಆಕ್ಷೇಪಣೆಗಳು ಬಂದಲ್ಲಿ ವ್ಯತ್ಯಾಸದ ಶುಲ್ಕವನ್ನು ಕಟ್ಟಡದ ಮಾಲಿಕರೇ ಭರಿಸಬೇಕಾಗುತ್ತದೆ.

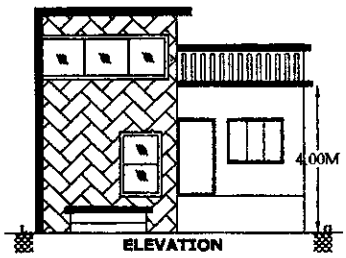

ELEVATION

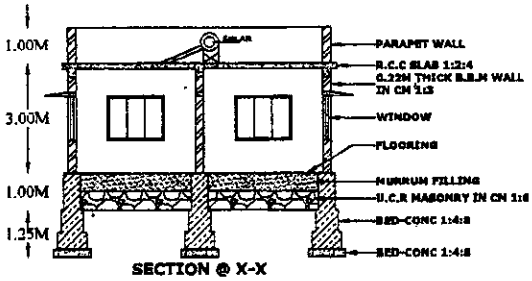

SECTION @ X-X

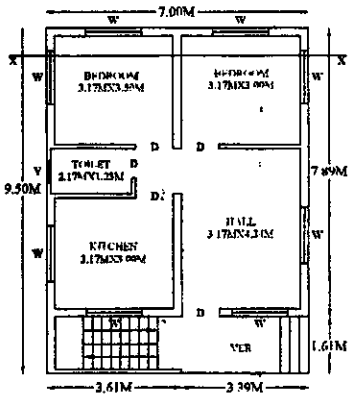

PROP. G.F PLAN
SCALE 1:100

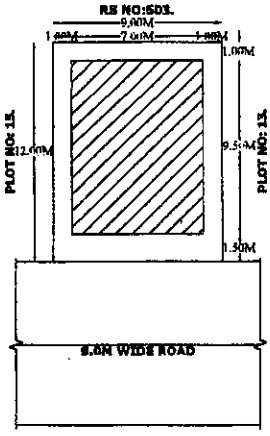

SITE PLAN
SCALE 1:200

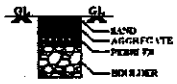

SECTION AT X-X

RAIN WATER HARVESTING PLAN

N

S.NO	PARTICULARS		SIZE	NO's
1.	DOOR	D	1.0MX2.1M	08
2.	WINDOW	W	1.0MX1.2M	08
3.	VENTILATORS	V	0.6MX0.6M	01

AREA STATEMENT

1.	PLOT AREA	: 108.00M2
2.	PROP.G.F.B.U.A	: 66.50M2
3.	F.A.R	: 0.61
4.	% COV	: 61.57%

STABILITY CERTIFICATE:THE G.F.BUILDING FOUNDATION DESIGNED TO THE LOAD OF G.F. SATISFACTORILY AS PER I.S 1978 SPECIFICATIONS.

PLAN OF A PROP.G.F RESIDENTIAL BUILDING BELONGING TO 1)SHRI:SIDDU URF SIDDAPPA SADASHIV BATAKURKI.
2)SHRI:SURESH BASAPPA MULLUR.
3)SHRI:YAMANAPPA RAMAPPA KOLI.

WITH RTC NO : 504/K, PLOT NO :14.

AT : MUDHOL. TQ : MUDHOL. DIST : BAGALKOT.

OWNERS SIGN:

ENGINEERS SIGN:

MDL-LBPAS-11857/25-26/BP

Building Permit Application (MDL-LBPAS-11857/25-26/BP) submitted by SIDDU URF SIDDAPPA SADASHIV BATAKURKI with Property ID 3655514, Survey No. 504/K

Owner(s)

1. SIDDU URF SIDDAPPA SADASHIV BATAKURKI (GULGALJAMBAGI)
2. SURESH BASAPPA MULLUR (MUDHOL)
3. YAMANAPPA RAMAPPA KOLI (JIRAGAL)

Land Details

1. Ward : 15 , Survey No. : 504/K , Plot No. : 14 , Area : 108.00 Sqm

Architect : Allabaksh Gaibusab Momin (KBPAS-REG-12100/20-21)

Layout Approved By : (Mr S B Patil [Asst Executive Engineer - MDL]) @ 11/10/2025 12:41:54

Approval Comments

Additional Comments

Verified

*** End of approval comments ***

Digitally signed by GOPAL KASE
Date: 2025.11.12 12:45:49 +05:30
Reason: Approved

भारत सरकार

आधार

ಭಾರತ ಸರ್ಕಾರ
Government of India

ಭಾರತೀಯ ವಿಶಿಷ್ಟ ಗುರುತು ಪ್ರಾಧಿಕಾರ
Unique Identification Authority of India

ನೋಂದಣಿ ಸಂಖ್ಯೆ/ Enrolment No.: 0000/00255/08324

To
ಚೇತನಕುಮಾರ ಗಣಿ
Chetankumar Gani
S/O Sangappa
Behind Teachers Colony Basavaling Nagar
Mudhol
Bagalkot Karnataka - 587313
9008727871

Signature valid
Digitally signed by UNIQUE IDENTIFICATION AUTHORITY OF INDIA
Date: 2022.[illegible] 07:43:57 UTC

ನಿಮ್ಮ ಆಧಾರ್ ಸಂಖ್ಯೆ / Your Aadhaar No. :
6364 2260 8993
VID : 9154 7678 9247 8200
ನನ್ನ ಆಧಾರ್, ನನ್ನ ಗುರುತು

ಭಾರತ ಸರ್ಕಾರ
Government of India

Issue Date: 24/01/2012

ಚೇತನಕುಮಾರ ಗಣಿ
Chetankumar Gani
ಜನ್ಮ ದಿನಾಂಕ/DOB: 20/07/1997
ಪುರುಷ/ MALE

6364 2260 8993
VID : 9154 7678 9247 8200
ನನ್ನ ಆಧಾರ್, ನನ್ನ ಗುರುತು

Government of India

AADHAAR

ಮಾಹಿತಿ

- ಆಧಾರ್ ಗುರುತಿನ ಪುರಾವೆಯೇ ಹೊರತು ಪೌರತ್ವದಲ್ಲ
- ಸುರಕ್ಷಿತ ಕ್ಯೂಆರ್ ಕೋಡ್/ಆಫ್ಲೈನ್ XML /ಆನ್ಲೈನ್ ದೃಢೀಕರಣ ಬಳಸಿ ಗುರುತನ್ನು ಪರಿಶೀಲಿಸಿ
- ಎಲೆಕ್ಟ್ರಾನಿಕ್ ಪ್ರಕ್ರಿಯೆ ಮೂಲಕ ಮುದ್ರಿತವಾದ ವಿದ್ಯುನ್ಮಾನ ದಾಖಲೆ ಇದಾಗಿದೆ

INFORMATION

- Aadhaar is a proof of identity, not of citizenship.
- Verify identity using Secure QR Code/ Offline XML/ Online Authentication.
- This is electronically generated letter.

- ಆಧಾರ್ ದೇಶದಾದ್ಯಂತ ಮಾನ್ಯತೆಯನ್ನು ಪಡೆದಿದೆ
- ಸುಲಭವಾಗಿ ಸರ್ಕಾರಿ ಹಾಗೂ ಸರ್ಕಾರೇತರ ಸೇವೆಗಳನ್ನು ಪಡೆಯಲು ಆಧಾರ್ ಸಹಾಯವಾಗಲಿದೆ.
- ನಿಮ್ಮ ಮೊಬೈಲ್ ಸಂಖ್ಯೆ ಮತ್ತು ಇ-ಮೇಲ್ ಐಡಿ ಅನ್ನು ಆಧಾರ್ ನಲ್ಲಿ ನವೀಕರಿಸಿಡಿ
- ಆಧಾರ್ ನ್ನು ನಿಮ್ಮ ಸ್ಮಾರ್ಟ್ ಫೋನ್ ನಲ್ಲಿ ಕೊಂಡೊಯ್ಯಿರಿ- mAadhaar ಅಪ್ಲಿಕೇಶನ್ ಬಳಸಿ

- Aadhaar is valid throughout the country.
- Aadhaar helps you avail various Government and non-Government services easily.
- Keep your mobile number & email ID updated in Aadhaar.
- Carry Aadhaar in your smart phone – use mAadhaar App.

ಭಾರತೀಯ ವಿಶಿಷ್ಟ ಗುರುತು ಪ್ರಾಧಿಕಾರ
Unique Identification Authority of India

ಆಧಾರ್

ವಿಳಾಸ:
S/O ಸಂಗಪ್ಪ, ಟೀಚರ್ಸ್ ಕಾಲೋನಿ ಹಿಂದುಗಡೆ
ಬಸವಲಿಂಗ ನಗರ, ಮುಧೋಳ, ಬಾಗಲಕೋಟ,
ಕರ್ನಾಟಕ - 587313

Address:
S/O Sangappa, Behind Teachers Colony
Basavaling Nagar, Mudhol, Bagalkot,
Karnataka - 587313

Download Date: 23/12/2022

6364 2260 8993

VID : 9154 7678 9247 8200

1947 | help@uidai.gov.in | www.uidai.gov.in